Poblacion de Argentina

Ideas de visualizacion

Heatmap - Estatico



Bar Plot por año - Estatico

Representacion de la cantidad de poblacion por region en los diferentes años

(Los nombres de las regiones NO van a ir a 45, el eje de poblacion estaria sincronizado en todos los graficos)

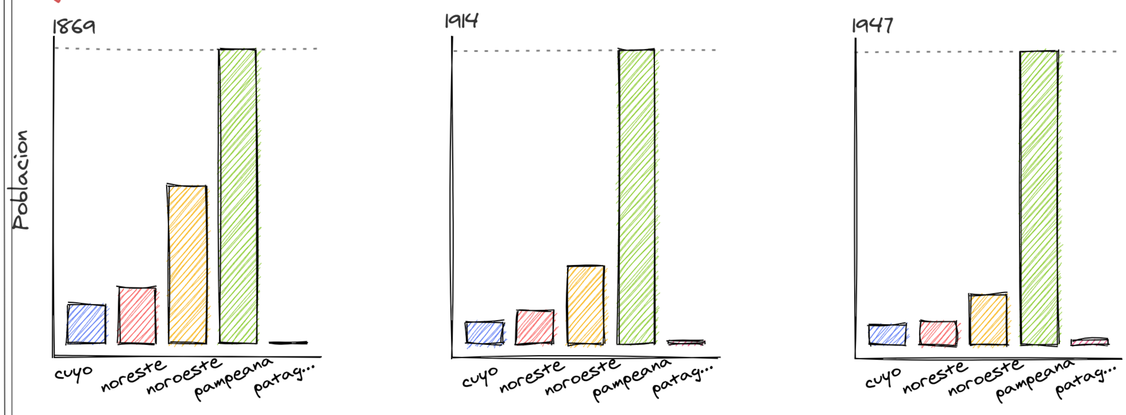

Choropleth or Bubble map - Dinamico
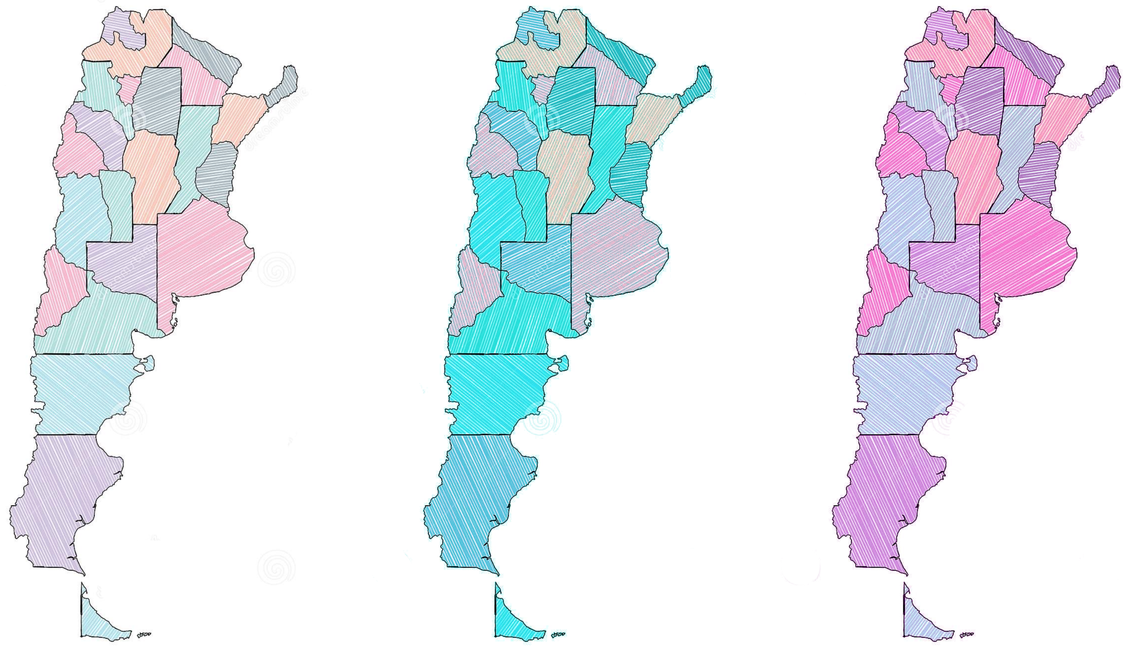
A medida que pasan los años, ir actualizando colores o burbujas